# AgriRetail

# 1 - Pressupostos

# 2 – Questões em Aberto

Ver quanto a isto as anotações em cada diagrama...

...no entanto, nesta modelação de referência não se dá destaque explícito a estes aspetos, pois o valor dos mesmos é o de ajudar a partilhar perspetivas e questões que resultam sempre em artefactos subjetivos da equipa de análise (dito de outra forma, qualquer formulação mais clara aqui de aspetos desta natureza iria sempre refletir perceções do corpo docente, portanto também subjetivas em si, logo um risco pedagógico para quem as fosse ler sem ter presente a companhia de um docente para as discutir...)

# 3 - Vista Geral (ArchiMate - layered view)

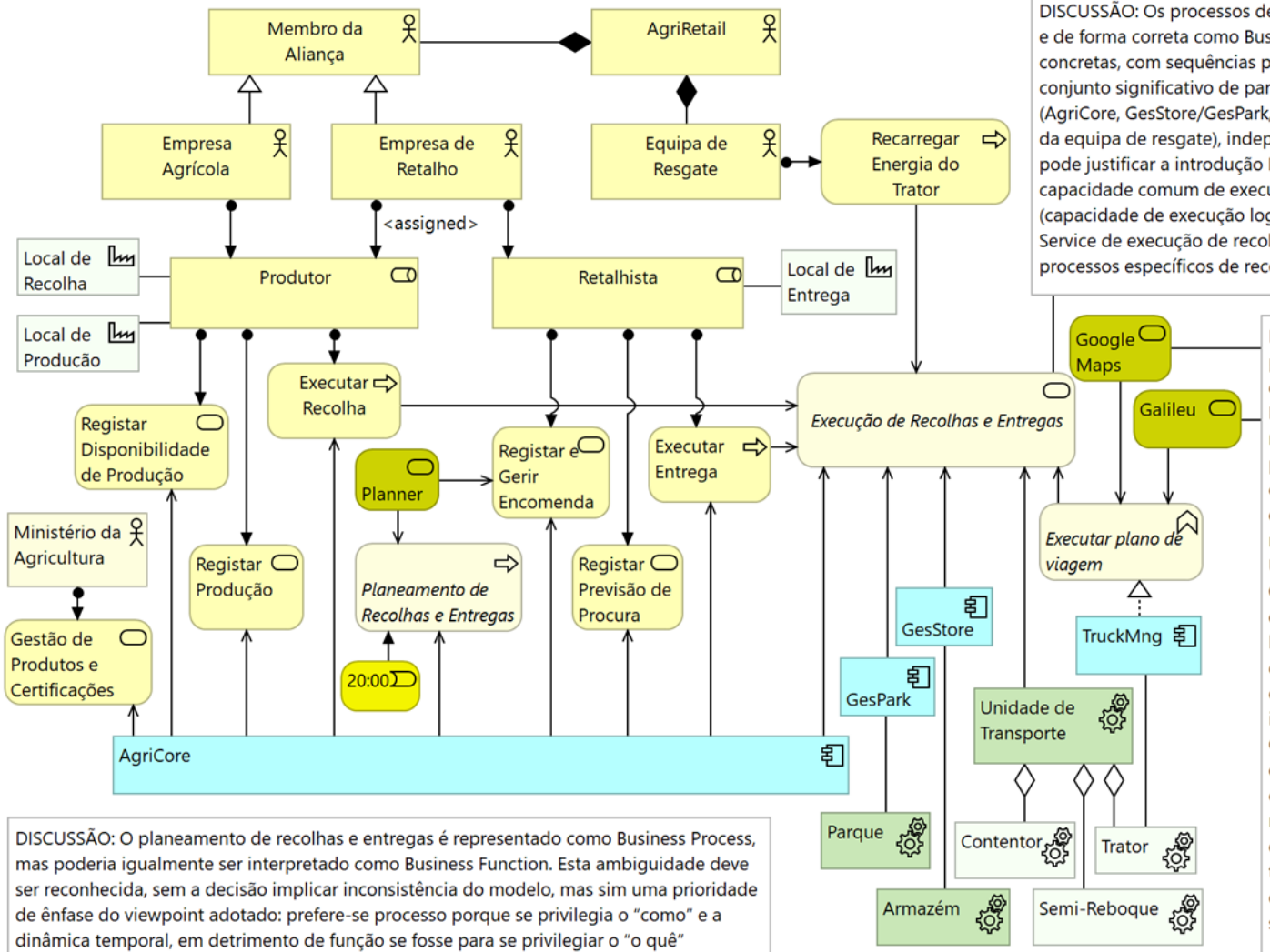


DISCUSSÃO: Os processos de recolha e de entrega são objetivamente definidos separados e de forma correta como Business Processes, pois correspondem a execuções operacionais concretas, com sequências próprias e sentidos distintos. No entanto, ambos partilham um conjunto significativo de participantes, responsabilidades e mecanismos transversais (AgriCore, GesStore/GesPark, Unidade de Transporte, tratamento de exceções e intervenção da equipa de resgate), independentemente de se tratar de recolha ou de entrega, o que pode justificar a introdução PRAGMÁTICA de um conceito agregador que represente essa capacidade comum de execução. Tal pode ser modelado como Business Function (capacidade de execução logística) ou, se encarado como oferta consumível, como Business Service de execução de recolhas e entregas, sendo no entanto sempre isso realizado pelos processos específicos de recolha e de entrega...

DISCUSSÃO: No UoD, o Planner é descrito explicitamente pelo seu papel no domínio de negócio (planeamento e decisão), o que fundamenta a sua interpretação como Business Service. Em contraste, Galileo e Google Maps são referidos pelo efeito que produzem (fornecimento de posicionamento e apoio à navegação), sem que o UoD clarifique a sua natureza tecnológica ou aplicacional. Embora exista conhecimento externo que permitiria uma classificação mais específica destes casos, é preciso ter cuidado, pois o UoD não refere explicitamente que isso deve ser considerado. Concluindo, quando um conceito é apresentado exclusivamente pelo seu valor direto para o negócio, a sua leitura como Business Service é metodologicamente defensável; quando é apresentado de forma ambígua, qualquer especialização arquitetural adicional constitui uma inferência externa ao UoD. Em consequência, a modelação de Galileo e Google Maps deve assumir que se trata de serviços externos, mas devendo a respetiva tipificação ser considerada provisória, assinalando a ambiguidade e a necessidade de clarificação futura com o cliente, pois pelo que nos é dado no UoD, nada nos garante que o cliente tenha o mesmo entendimento de Google Maps ou de Galileu que o analista teria, logo qualquer inferência do analista deve ser sempre assinalda como subjetiva!

DISCUSSÃO: O planeamento de recolhas e entregas é representado como Business Process, mas poderia igualmente ser interpretado como Business Function. Esta ambiguidade deve ser reconhecida, sem a decisão implicar inconsistência do modelo, mas sim uma prioridade de ênfase do viewpoint adotado: prefere-se processo porque se privilegia o "como" e a dinâmica temporal, em detrimento de função se fosse para se privilegiar o "o quê" enquanto competência estável do negócio... mas devia-se clarificar com o cliente!

DISCUSSÃO: Na ausência de requisitos funcionais ou não funcionais (RNFs) que fundamentem ligar aplicações ao AgriCore, isso deve ser omitido, pois seria explicitar uma integração técnica presumida, não uma relação de valor. Sem rasto claro para serviços, processos ou objetivos de negócio, essas associações não acrescentam significado arquitetural e introduziriam ruído, sendo o mais o correto omiti-las neste viewpoint.

DISCUSSÃO: No UoD, os pares GesPark / Parque e GesStore / Armazém distinguem explicitamente um sistema lógico de gestão local de um elemento físico, sendo essa separação arquiteturalmente relevante quando ajuda a explicitar responsabilidades e a articulação com o AgriCore. Já conceitos como "Local de Recolha" ou "Local de Entrega" surgem sobretudo como papéis contextuais nos processos, não como entidades estruturais autónomas, pelo que a sua representação no diagrama de camadas tende a não acrescentar valor adicional. De forma análoga, componentes internas da Unidade de Transporte só devem ser explicitadas quando contribuem para clarificar serviços ou dependências relevantes; caso contrário, o detalhe deve ser remetido para viewpoints mais técnicos...

# 4 - Processo de Recolha

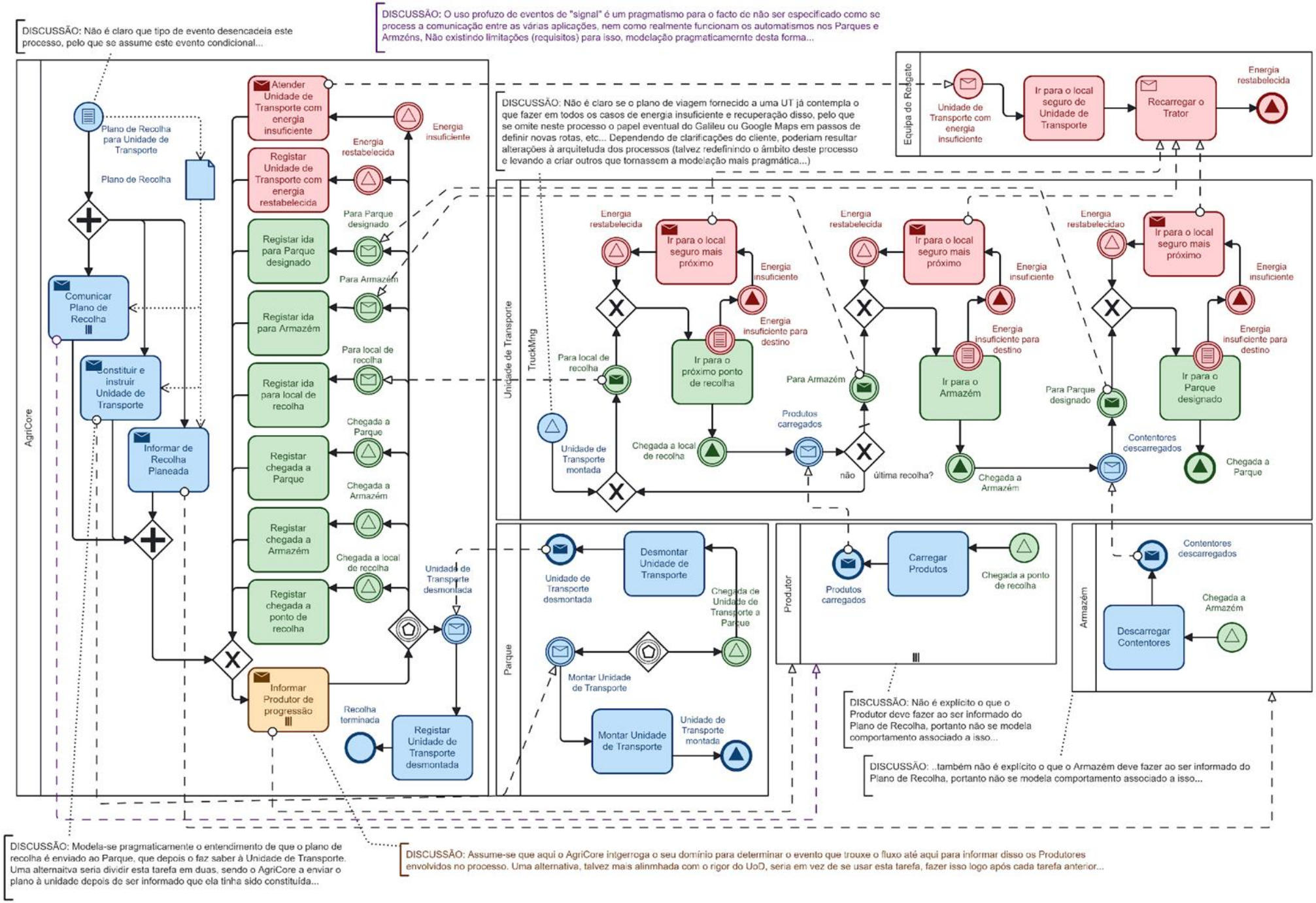

# 5 – AgriCore Casos de Uso

**7 – AgriCore - Caso de Uso "Registar Encomenda" - Cenários**

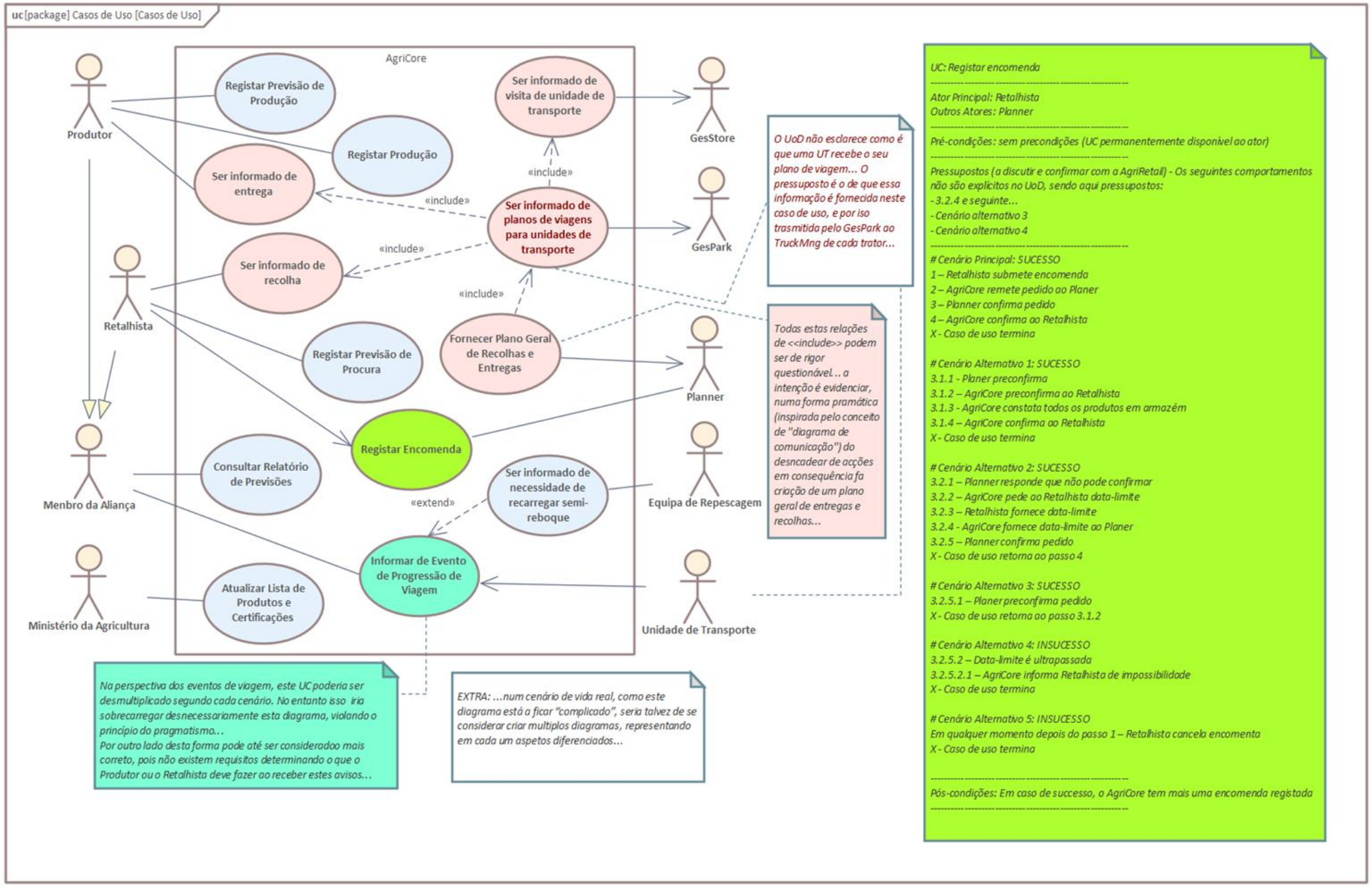

# 6 – AgriCore - Modelo de Domínio

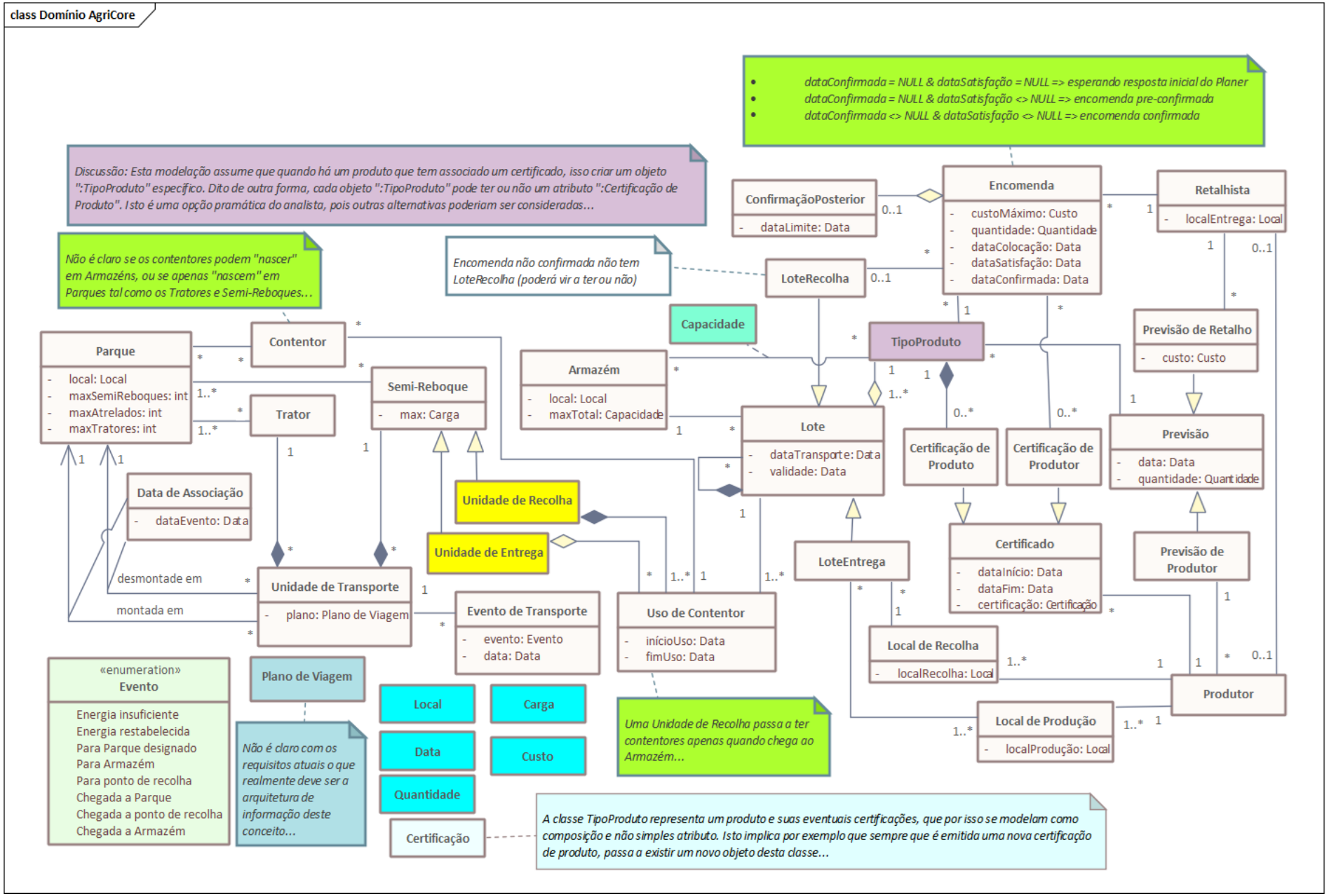

# 8 – AgriCore - Casos de Uso
# "Registar Encomenda" – Diagrama de SEQ

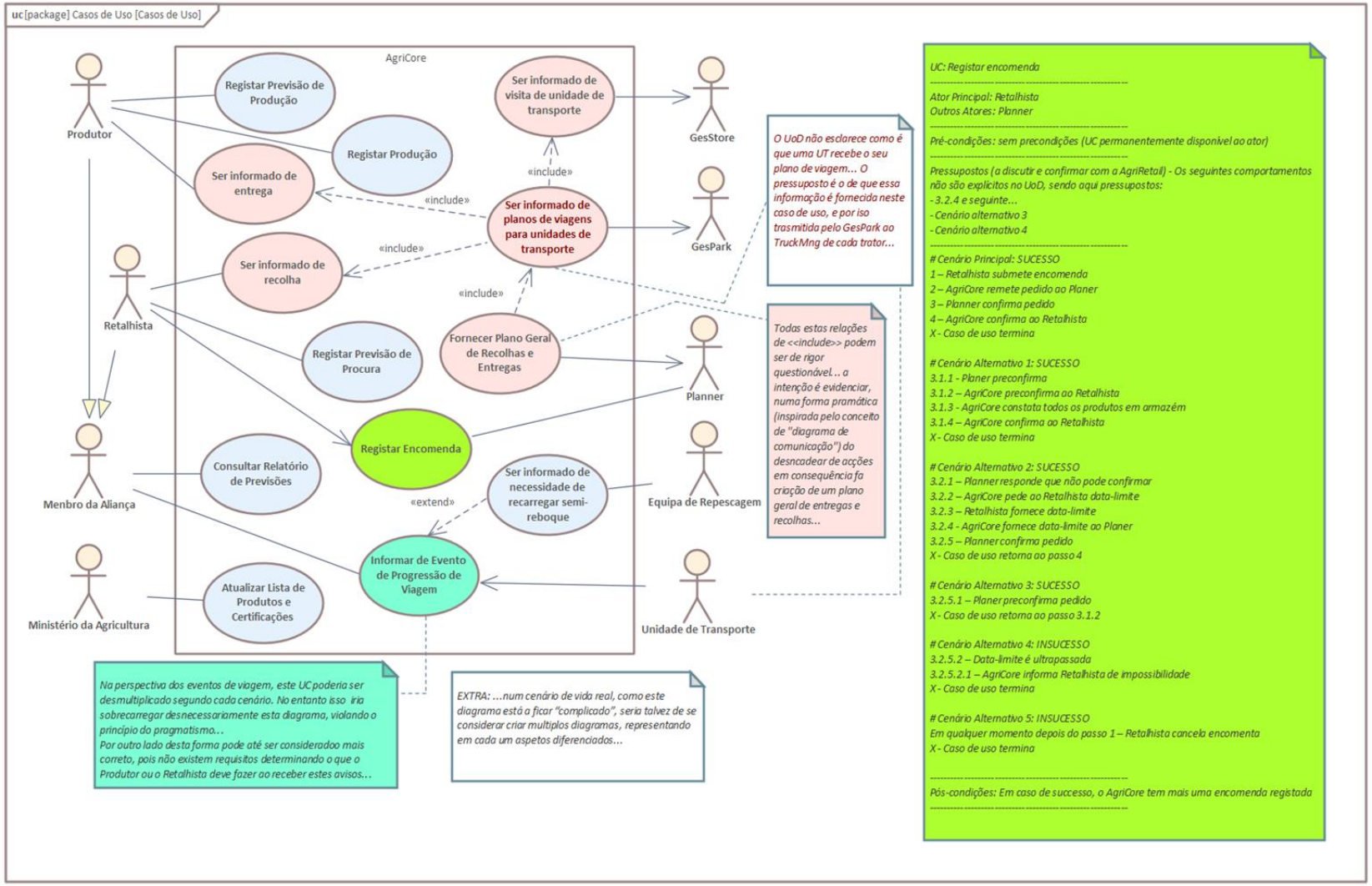


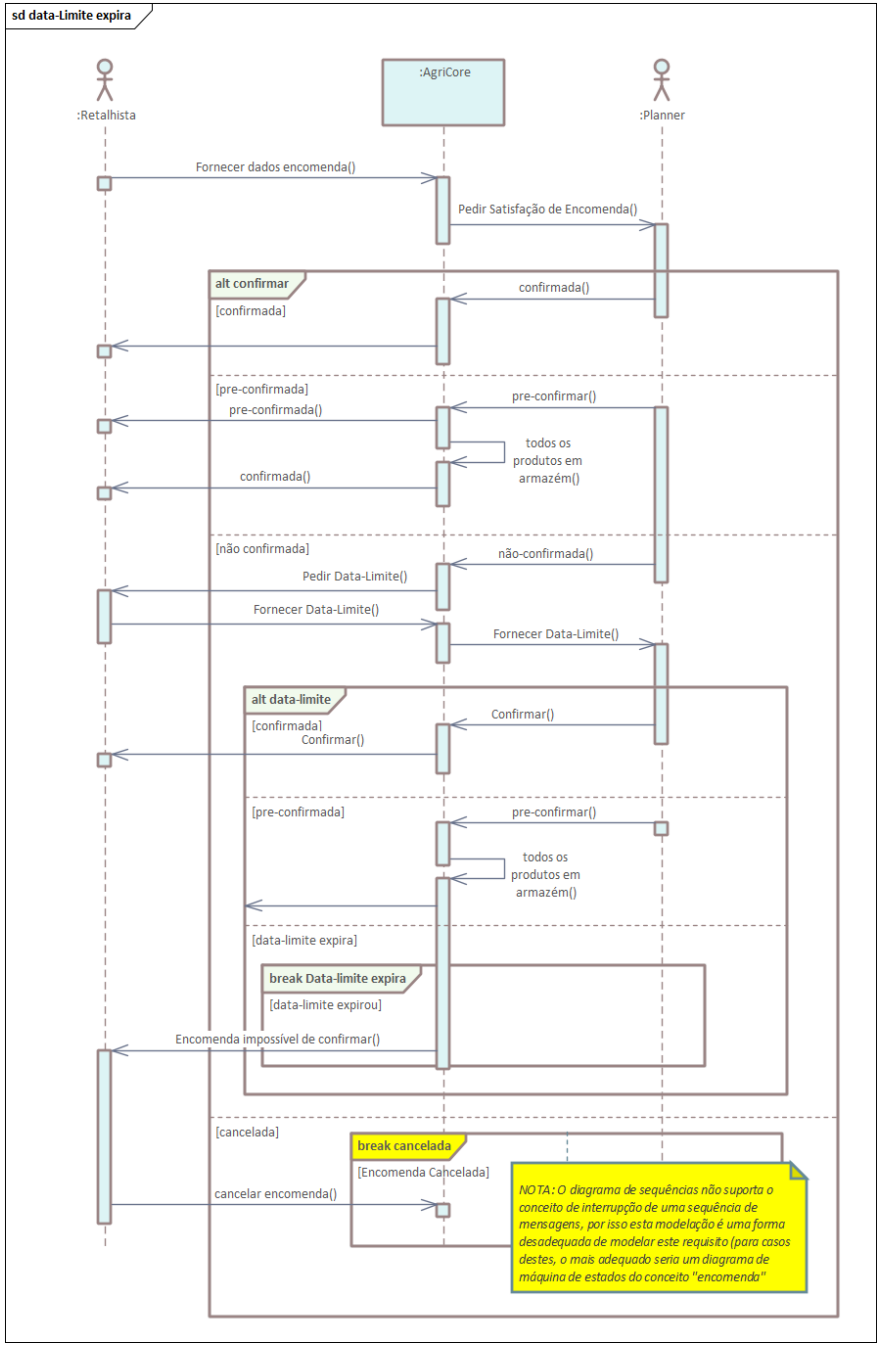

# 9 – STM ~~Semi-Reboque~~ => UT

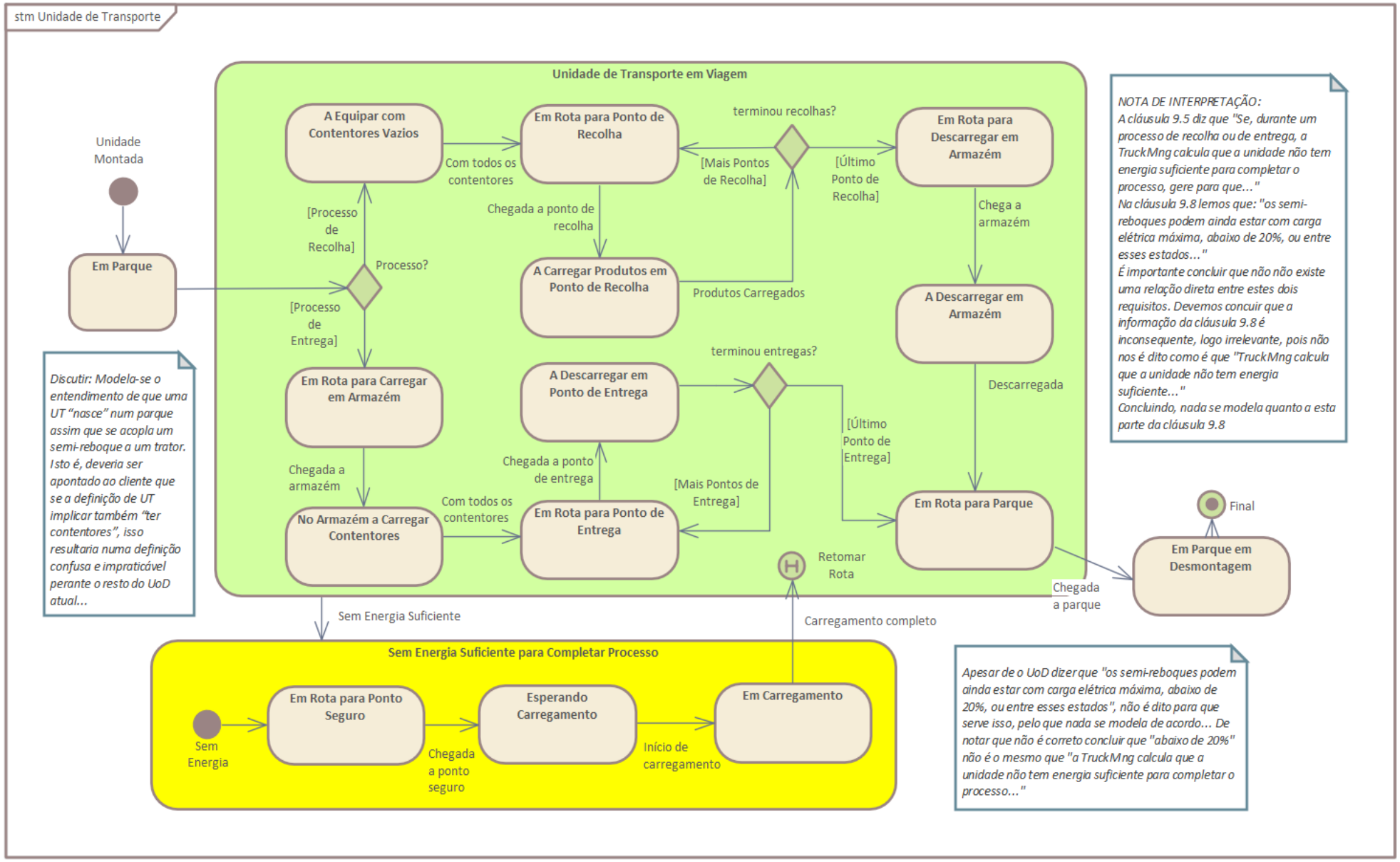

# 10 – Unidade de Transporte / TruckMng UC

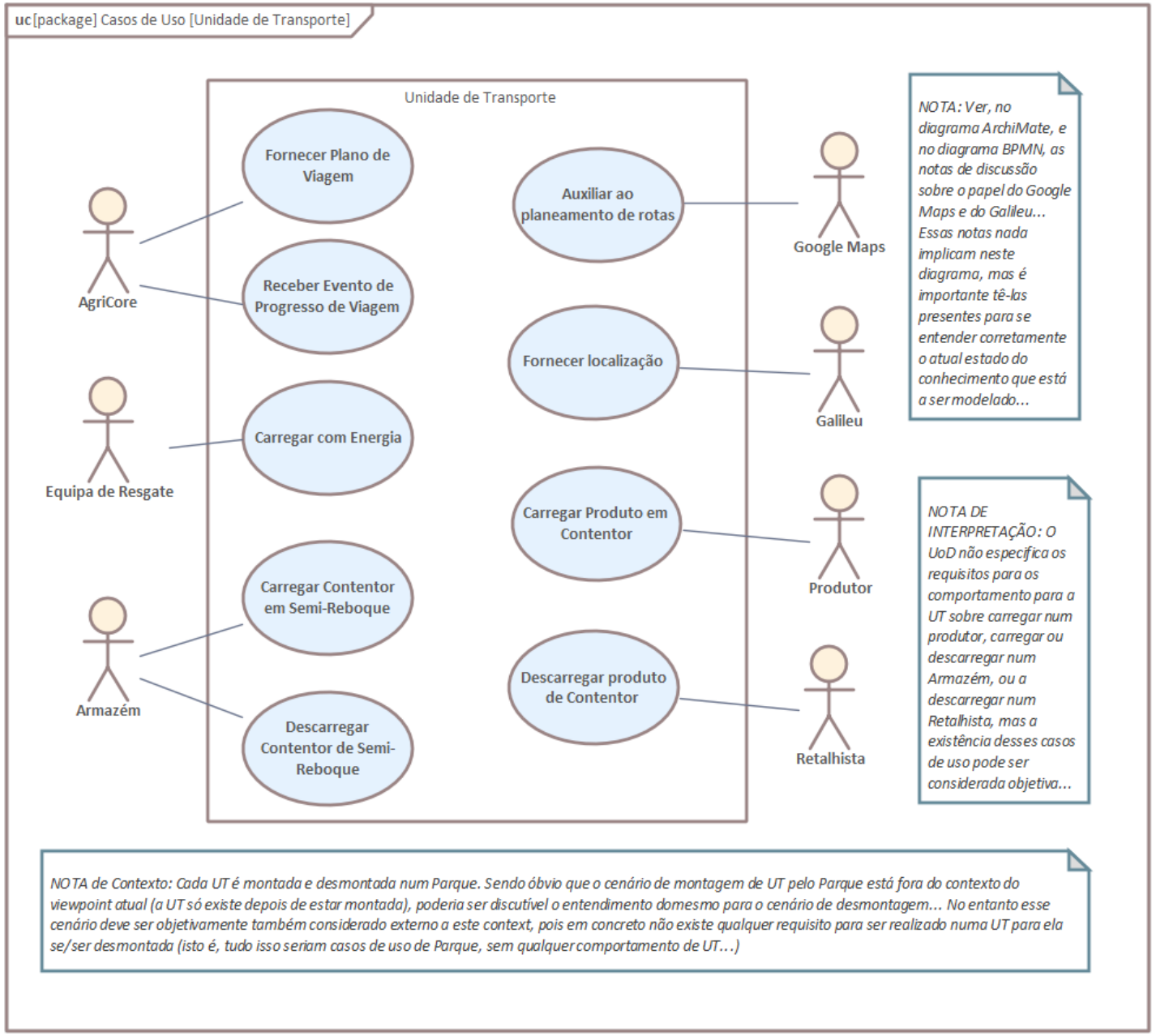

# 11 – Unidade de Transporte / TruckMng BDD

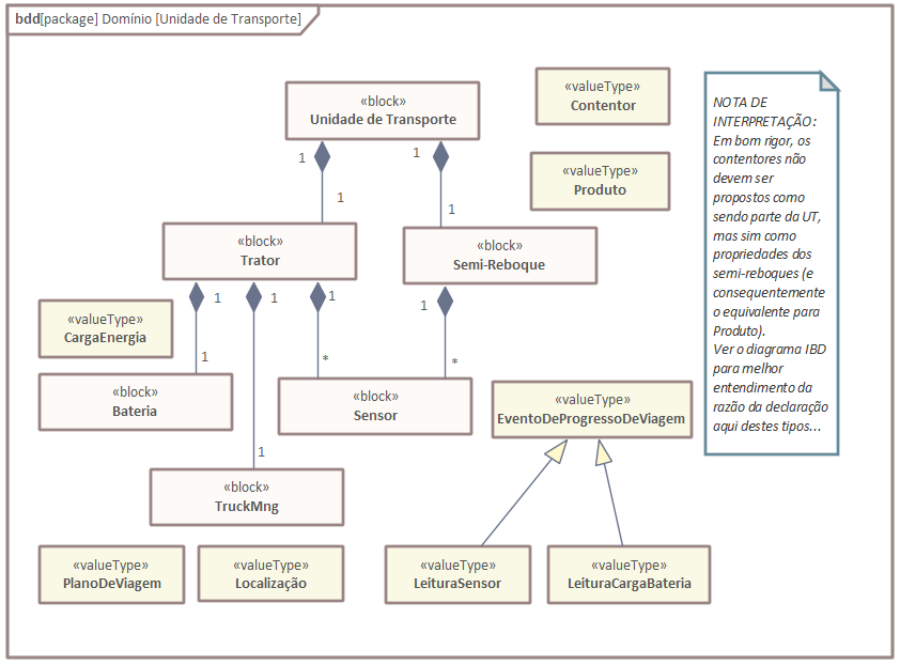

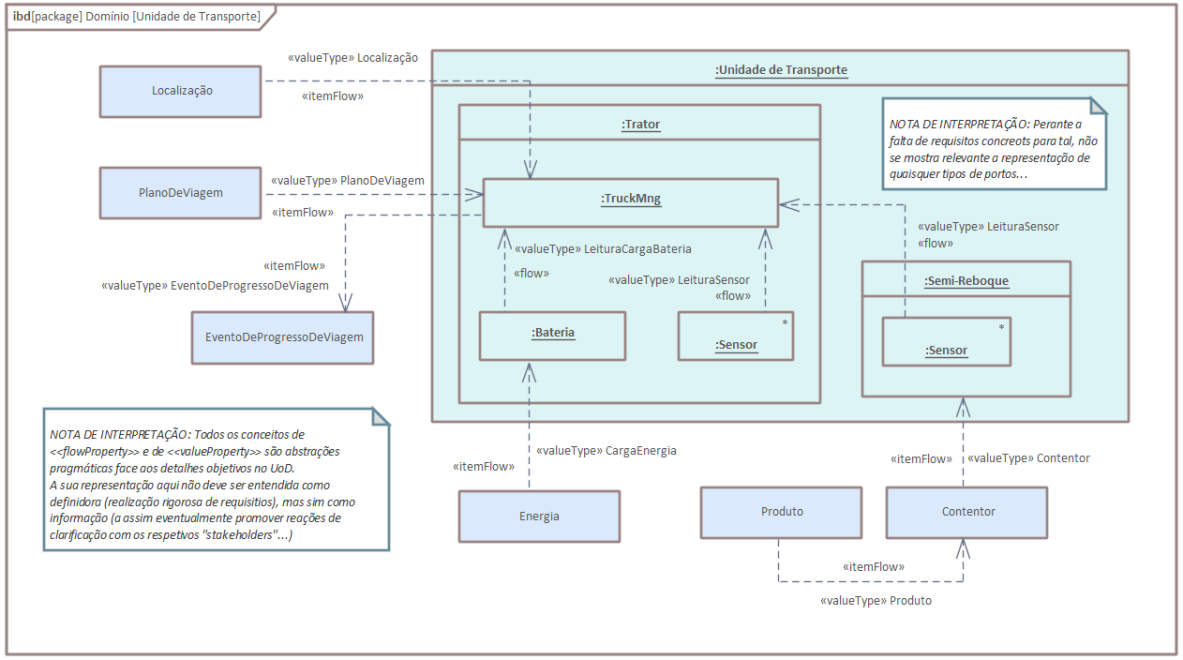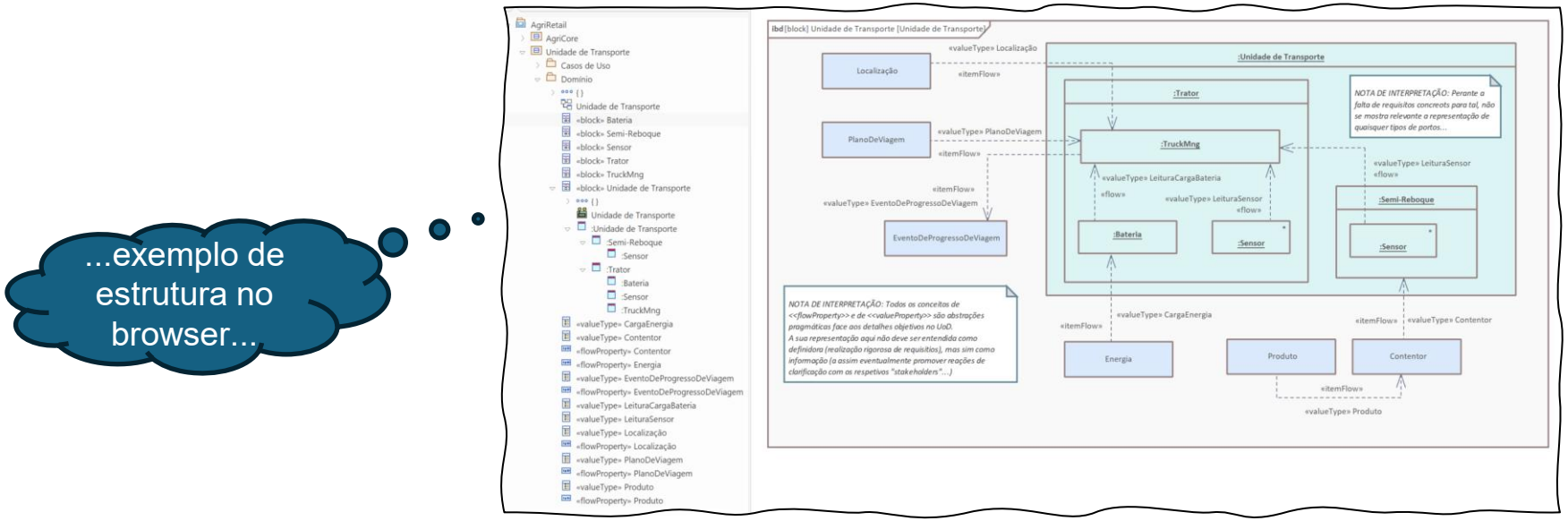
# 12 – Unidade de Transporte / TruckMng ibd